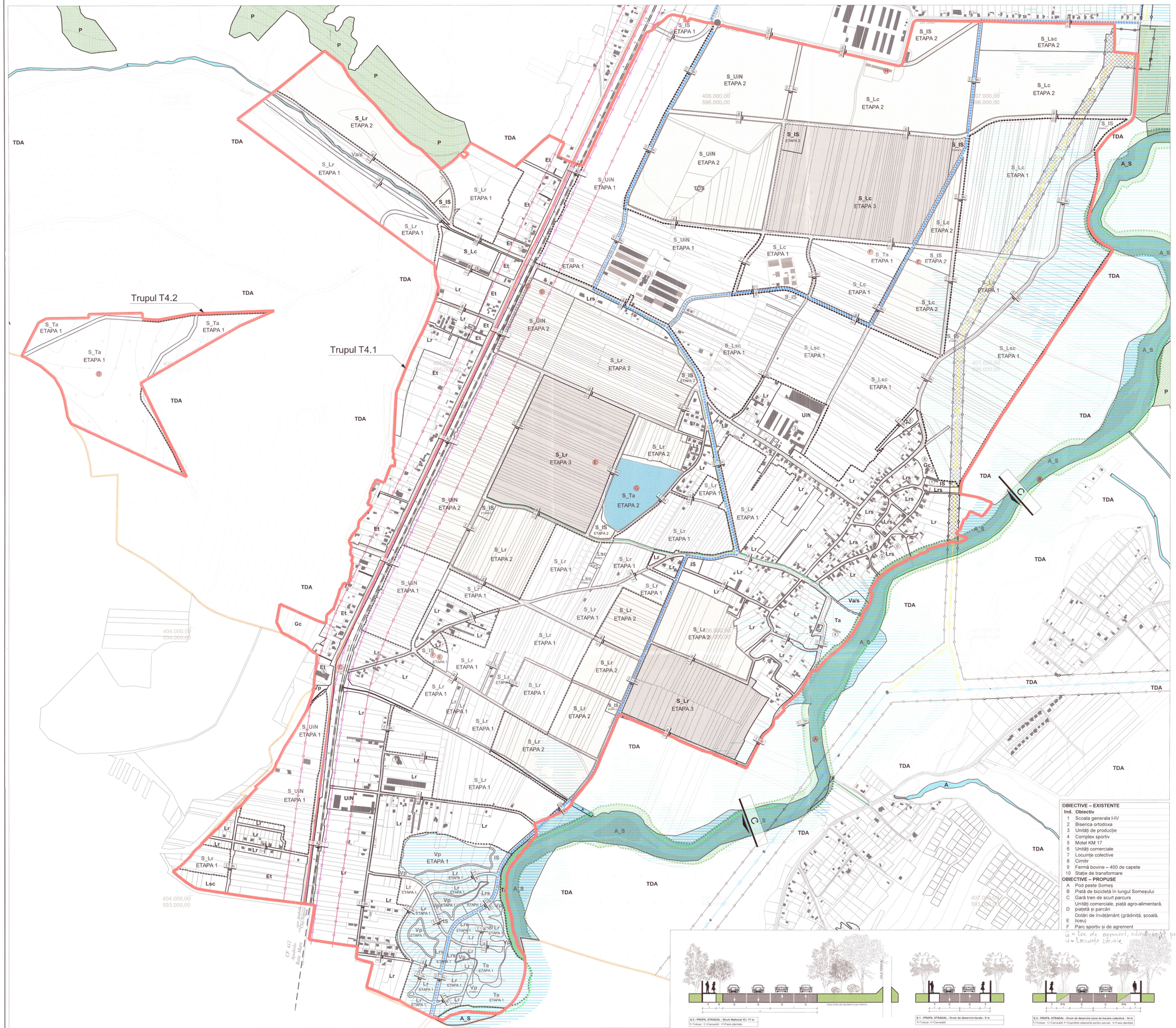
6.4 Reglementări urbanistice - UTR, sat Jucu de Mijloc

REACTUALIZARE
P.U.G
COMUNA JUCU
JUDEȚUL CLUJ

N, NE, E, SE, S, SV, V, NV

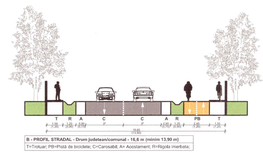


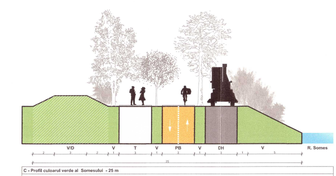
BILANȚUL TERITORIAL AL SUPRAFETELOR CUPRINSE IN INTRAVILAN

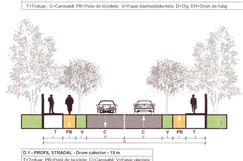
Zona functionala	Situatia existenta Suprafata HA	%	Situatia propusa Suprafata HA	%
Locuințe si functiuni complementare	150.84	74.66%	438.93	61.33%
• Locuințe rurale			*268.74*	*37.55%*
• Locuințe colective	-	-	*104.13*	*14.55%*
• Locuințe semicolective	-	-	*66.06*	*9.23%*
Zona mixta – locuințe si servicii	-	-	11.69	1.63%
Activități economice cu caracter terțiar	-	-	28.73	4.01%
Unitati industriale si depozitare	22.70	11.24%	103.52	14.46%
• Parc industrial	-	-	*0.00*	*0.00%*
• Producție industriala cu caracter nepoluant	-	-	*103.52*	*14.46%*
Unitati agro-zootehnice	3.00	1.48%	0.00	0.00%
Institutii si servicii de interes public	1.60	0.79%	12.15	1.70%
Cai de comunicatie si transport, din care:	12.00	5.94%	67.90	9.49%
• rutier	12.00	*5.94%*	*60.41*	*8.44%*
• feroviar	-	-	*7.49*	*1.05%*
Spatii verzi, sport, agrement, protectie	5.80	2.87%	43.20	6.05%
• Zone verzi cu acces public nelimitat	-	-	*5.89*	*0.82%*
• Zone verzi de protectie	-	-	*2.93*	*0.41%*
• Zona de agrement publica/privat	-	-	*34.46*	*4.82%*
Constructii tehnico-edilitare	-	-	0.00	0.00%
Gospodarie comunala-cimitire	3.50	1.73%	2.67	0.37%
Destinatie speciala	0.00	-	0.04	0.01%
Ape	2.60	1.29%	6.77	0.95%
TOTAL	***202.04***	***100.00%***	***715.68***	***100.00%***

UNITĂȚI TERITORIALE DE REFERINȚĂ ÎN EXTRAVILAN	
TDA	Terenuri cu destinație agricolă
A	Terenuri aflate permanent sub ape
A_S	Zonă cu rol de culoar ecologic și turistic aferent Someșului
P	Terenuri cu destinație forestieră
TDS	Terenuri cu destinație specială
UNITĂȚI TERITORIALE DE REFERINȚĂ ÎN INTRAVILAN	
Lr	Zonă de locuințe rurale
S_Lr	Zonă de sistematizare pentru locuințe rurale
Ls	Zonă de locuințe sociale
Lsc	Zonă de locuințe semicolective
S_Lsc	Zonă de sistematizare pentru locuințe semicolective
Lc	Zonă locuințe colective
S_Lc	Zonă de sistematizare pentru Locuințe colective
IS	Zonă de instituții publice și servicii
S_IS	Zonă de sistematizare pentru instituții publice și servicii
Lrs	Zonă mixtă de locuințe rurale și servicii
Ta	Zonă de turism și agrement
S_Ta	Zonă de sistematizare pentru turism și agrement
S_LTa	Zonă de sistematizare pentru locuințe și turism / agrement
Et	Zonă de activități economice cu caracter terțiar
Ui/d	Zonă de unități industriale și depozitare
UiN	Zonă de unități industriale mici cu caracter nepoluant
S_UiN	Zonă de sistematizare pentru unități industriale mici cu caracter nepoluant
Ua	Zonă de unități agricole
Vp	Zonă verde cu rol de protectie și coridor ecologic
Va/s	Zonă verde de agrement și sport
Gc	Zonă gospodărire comunală
E	Zonă aferentă construcțiilor tehnico-edilitare
TDS	Zonă cu destinație specială
TDS-Mapn	Zonă cu destinație specială- MAPN
Ccr	Zonă căi de comunicație rutieră și amenajări aferente
Ccf	Zonă căi de comunicație feroviară și amenajări aferente

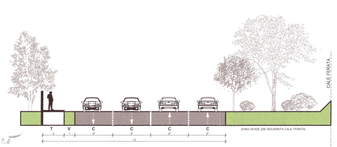
OBIECTIVE – EXISTENTE	
Ind.	**Obiectiv**
1	Scoala generala I-IV
2	Biserica ortodoxa
3	Unități de producție
4	Complex sportiv
5	Motel KM 17
6	Unități comerciale
7	Locuințe colective
8	Cimitir
9	Fermă bovine – 400 de capete
10	Statie de transformare
OBIECTIVE – PROPUSE	
A	Pod peste Someș
B	Pistă de bicicletă în lungul Someșului
C	Gară tren de scurt parcurs
D	Unități comerciale, piață agro-alimentară, piatetă și parcări
E	Dotări de învățământ (grădiniță, școală, liceu)
F	Parc sportiv și de agrement

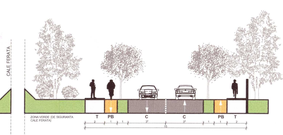

B - PROFIL STRADAL - Drum judetean/comunal - 18,6 m (minim 13,90 m)
T=Trotuar; PB=Pista de bicicleta; C=Carosabil; Ar- Aco;amenaj. H=Rigola marginala


C - Profil culoarul verde al Somesului - 29 m
T=Trotuar; C=Carosabil; PB=Pista de bicicleta; V=Fasie biarbo/aliniamente; D=Dig; DH=Drum de halaj


D.1 - PROFIL STRADAL - Drum colector - 15 m
T=Trotuar; PB=Pistă de bicicletă; C=Carosabil; V=Fasie plantată;

CONSILIUL JUDEȚEAN CLUJ
ANEXĂ
Nota nr. 39 din 19.07.2021
VIZAT SPRE NESCHIMBARE
ARHITECT ȘEF

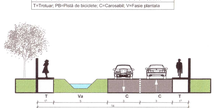

A.1 - PROFIL STRADAL - DN 1C, Calea ferata si Drum colector
T=Trotuar; PB=Pistă de bicicletă; C=Carosabil; V=Fasie plantata



A.2 - PROFIL STRADAL - Drum National 1C- 17 m
T=Trotuar; C=Carosabil; V=Fasie plantata

E.1 - PROFIL STRADAL - Drum de deservire locala - 9 m
T=Trotuar; C=Carosabil

E.2 - PROFIL STRADAL - Drum de deservire zona de locuire colectivă - 14 m
T=Trotuar; C=Carosabil; P=Suprafețe adiacente pentru parcari; V=Fasie plantată


E.3 - PROFIL STRADAL - Drum de deservire locală - 14 m
T=Trotuar; C=Carosabil; P=Suprafețe adiacente pentru parcari; V=Fasie plantata; Va=Valc

LEGENDĂ

LIMITE
- Limita UAT Jucu
- Limita intravilan propus
- Limita zonei centrale
- Limita unităților teritoriale de referință (UTR)

DRUMURI
- Drum național
- Drum județean
- Traseu propus Someș Expres
- Străzi, ulițe, drumuri de exploatare
- Străzi propuse spre modernizare/propuse
- Traseu propus : Transportul în comun- Autobuz

ZONE CU RISCURI NATURALE
- Zona cu risc de inundabilitate 1%
- Zona cu risc de inundabilitate 5%
- Zona cu potențial de alunecare moderat

ZONE PROTEJATE ȘI ZONE DE PROTECȚIE
- Sit de importanță comunitară Natura 2000
- Zonă de protecție sanitară (surse de apă, înmagazinări, stații de epurare ape uzate, ferme agrozootehnice, etc.)
- Zonă de protecție față de construcții și culoare tehnice (stații electrice, linii de înaltă tensiune, rețele de gaze, etc.)
- Zonă de protecție față de infrastructura feroviară (100 metri din axul caii ferate)
- Zona de siguranță față de infrastructura feroviară (20 metri din axul caii ferate)
- Culoarul verde al Someșului (drum de halaj, pistă de bicicliete, traseu pietonal, dig și zone de relaxare)

LUCRĂRI TEHNICO-EDILITARE
- Linie electrică aeriană LEA 400kV
- Linie electrică aeriană LEA 110kV

ETAPIZARE
- ETAPA 1
- ETAPA 2
- ETAPA 3

Acest document este proprietatea intelectuală a arhitectului proiectant și nu poate fi folosit, reprodus sau transmis în format electronic sau pe orice alt suport fără acordul scris al acestuia. Documentul nu are valoare contractuală. Informațiile din acest document nu pot fi folosite în scopuri publicitare fără acordul scris al proiectantului. Nerespectarea acestor condiții ne rezervă dreptul de a lua măsurile legale care se impun.

SEF PROIECT	arh. Horaţiu Racasan		PROIECTANT S.C. RAUM S.R.L. Str. Octavian Goga, nr. 41, Cluj-Napoca, jud. Cluj, Romania e-mail: raumoffice@gmail.com arh. Horaţiu Răcăşan tel. 0723-624272 membru O.A.R. / membru R.U.R.
PROIECTAT	arh. Crina Petca		
DESENAT	arh. Crina Petca		
VERIFICAT	arh. Horaţiu Racasan		BENEFICIARI COMUNA JUCU reprezentata prin Pojar Valentin Dorel
DENUMIREA PLANSEI		NR. PLANSA / SCARA	NR. PROIECT
Reglementări urbanistice - UTR, sat Jucu de Mijloc		6.4	42
FAZA	SCARA	DATA	DENUMIREA LUCRARII:
PUG	1:5000	2020	REACTUALIZARE PLAN URBANISTIC GENERAL (PUG) COMUNA JUCU, JUD. CLUJ